物件概要書（事業用地・他）

物件名称	市原市東国分寺台二丁目		
物件所在地	市原市東国分寺台二丁目２番７		
現況	更地　※上物解体済		
地目	山林/所有権		
地積	（公簿）1037㎡（約313.69坪）/　（実測）1037.38㎡（約313.80坪）		
建物	~~構造~~		
	~~延床面積~~		
	~~築年月~~		
価格	金１４１，０００，０００円（約４５万円）　※公簿面積にて計算		
用途地域	第一種住居地域/第一種低層住居専用地域		
建蔽率	下記備考欄参照	容積率	下記備考欄参照
その他規制	景観法，特定盛土等規制法，都市再生特別措置法，建築基準法第22・23条区域		
道路幅	北西側幅員　約２２ｍ（公道）　東南側幅員　約６ｍ（公道）		
交通	JR内房線五井駅（約4,200m）※グーグルマップより		
引渡し	即時可		
その他	●建蔽率及び容積率について（建蔽率/容積率） 第一種住居地域　60%/200% 第一種低層住居専用地域　50%/100% ●高度制限 第一種住居地域　第一種高度地区 第一種低層住居専用地域　高さ制限10m ●設備　公営水道・都市ガス・下水 ●確定測量済（地積更正登記は行いません。） ●分割購入相談応		

千葉県市原市東国分寺台1丁目12-18付近

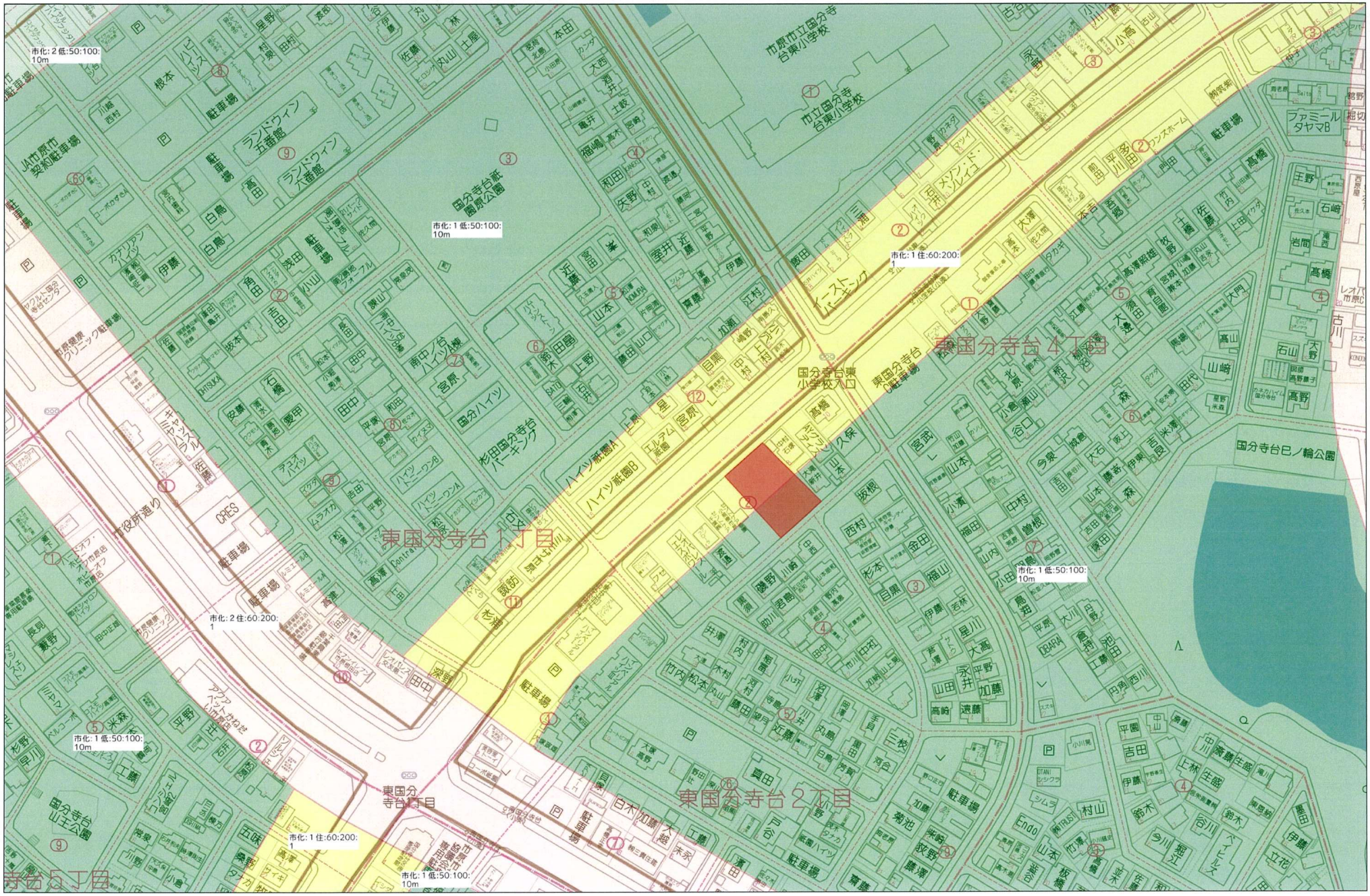

80m

1:1715

禁無断複写複製

Copyright(C)2026 ZENRIN CO., LTD.

千葉県市原市東国分寺台2丁目2-14付近

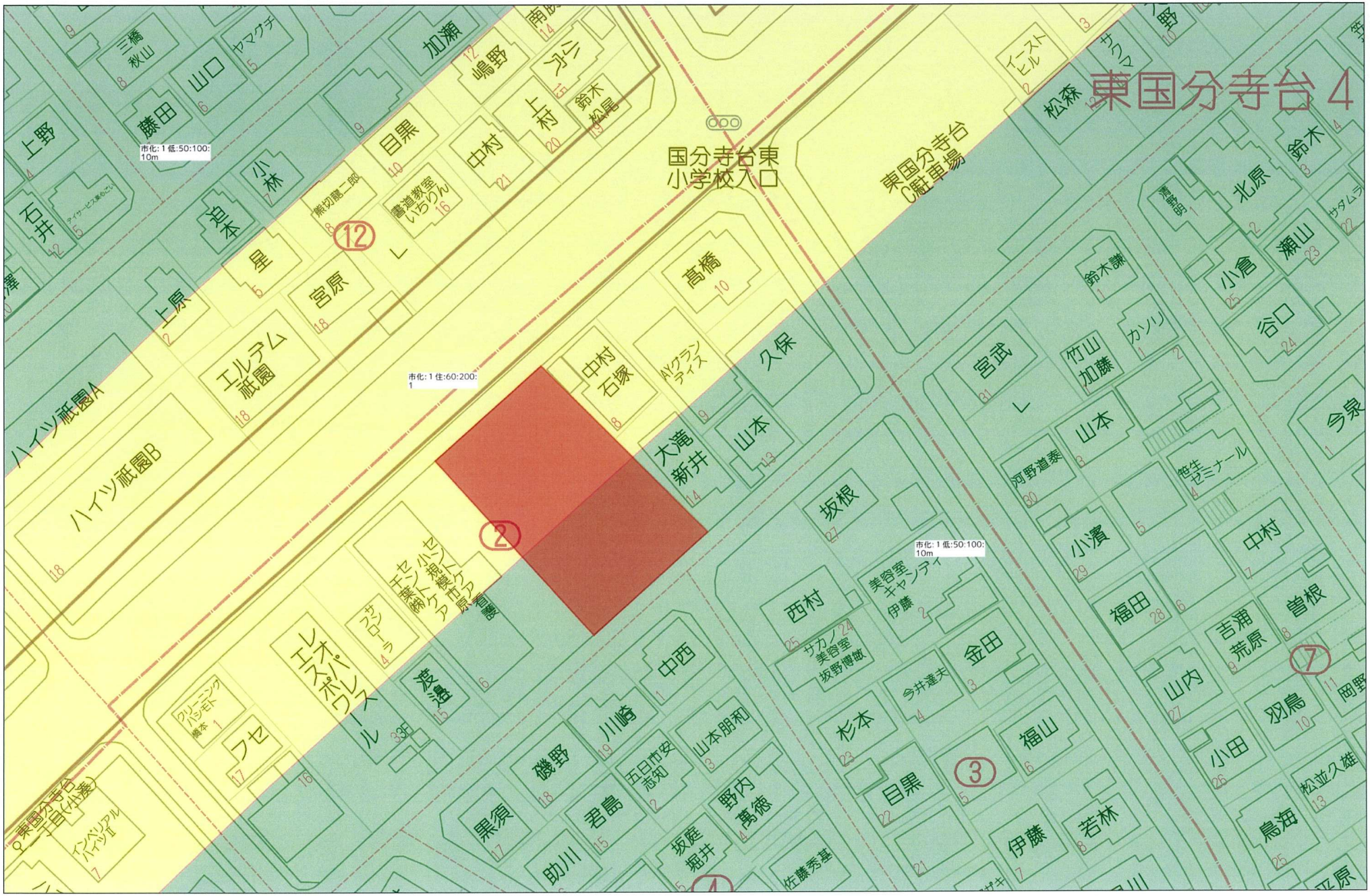

40m

1:606

禁無断複写複製

Copyright(C)2026 ZENRIN CO., LTD.

表示年月日：２０２６／０３／１３

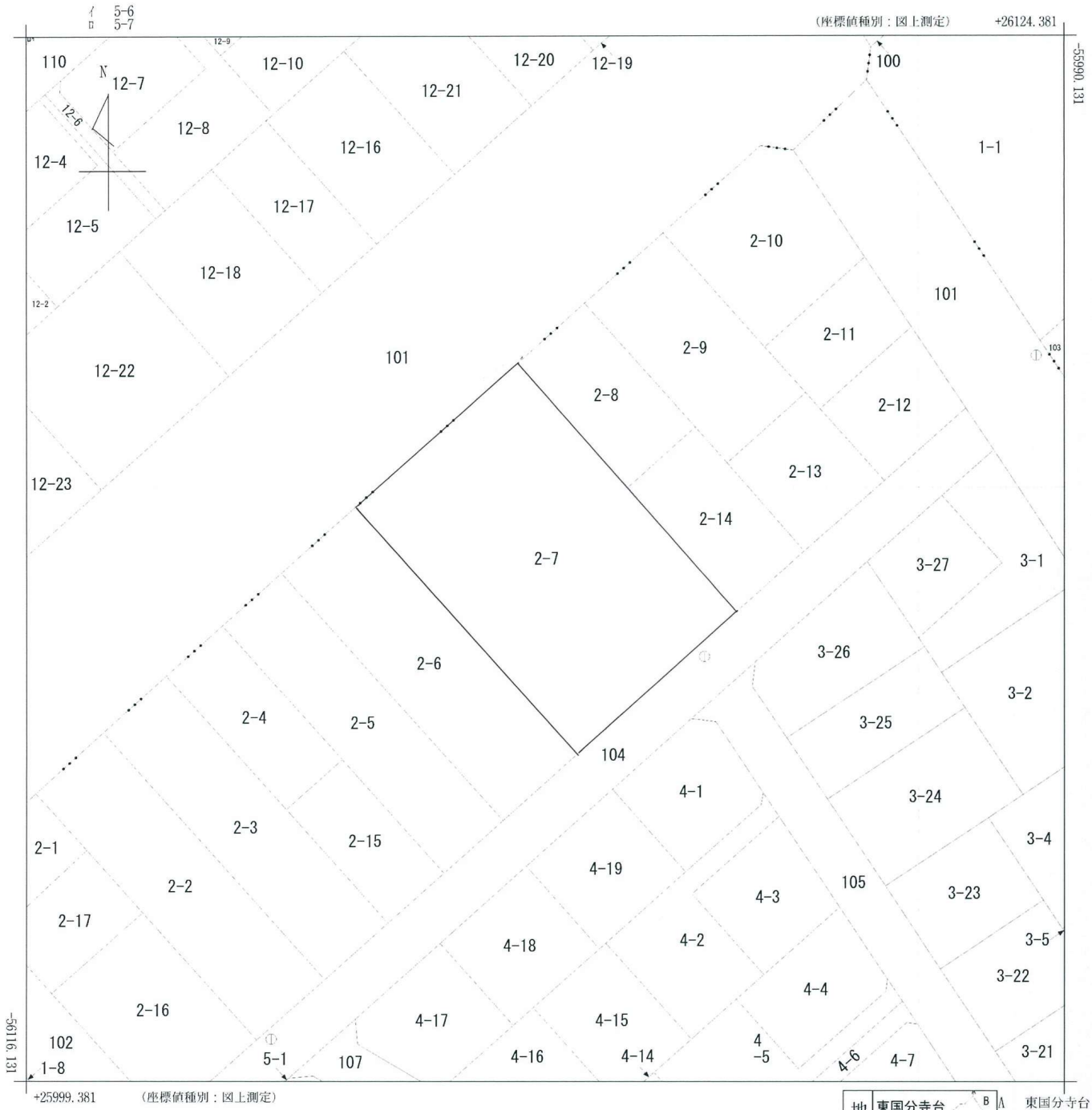

（注）国土交通省国土地理院が公表した座標補正パラメータ（touhokutaihciyouoki2011.par）による修正がされています。

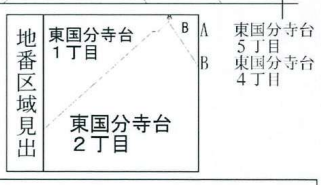

請求部分	所　在	市原市東国分寺台二丁目					地　番	2番7	
出力縮尺	1/500	精度区分	甲一	座標系番号又は記号	Ⅸ	分類	地図（法第１４条第１項）国調法１９－５指定	種類	土地区画整理所在図
作成年月日	平成10年5月2日			備付年月日（原図）				補記事項	

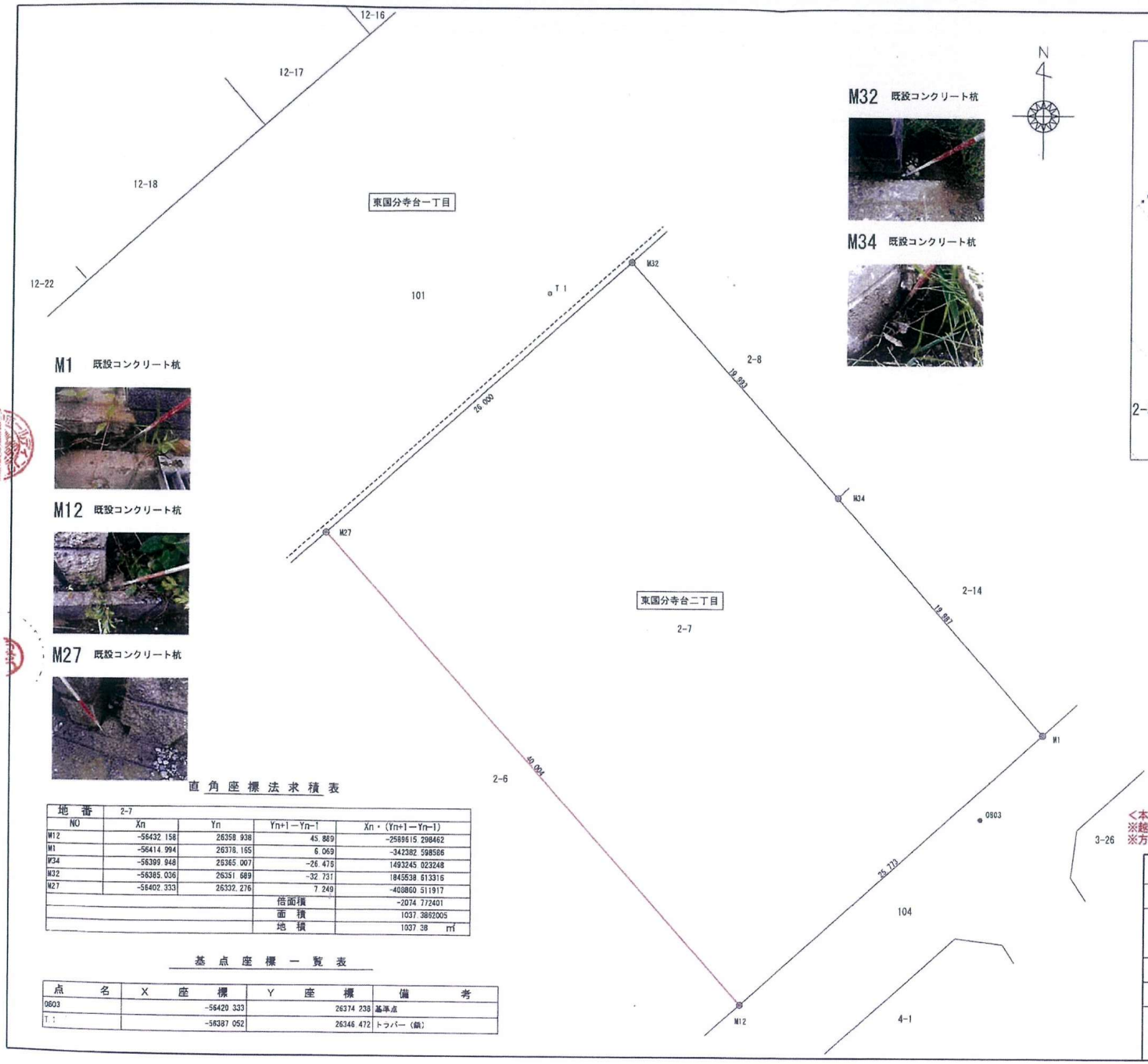

M32 既設コンクリート杭

M34 既設コンクリート杭

M1 既設コンクリート杭

M12 既設コンクリート杭

M27 既設コンクリート杭

公図写し 縮尺1：500

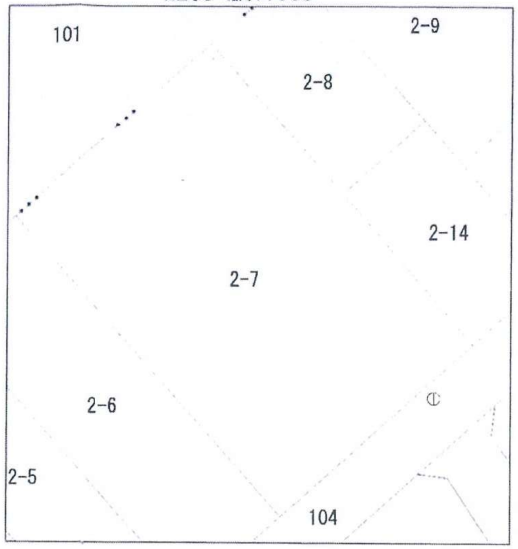

境界点	境界標の種類
⊠	石杭
◎	コンクリート杭
◇	金属標
⊞	プラスチック杭
⊗	鋲
⊡	木杭
○	赤ペイント・計算点
⊙	刻み印
●	基準点

<本図作成の前提条件および取扱上の注意事項>
※越境物の確認は目視によるものです。
※方位は真北測定によるものではありません。

直角座標法求積表

地番	2-7			
NO	Xn	Yn	Yn+1－Yn-1	Xn・(Yn+1－Yn-1)
M12	-56432.158	26358.938	45.889	-2589615.298462
M1	-56414.994	26378.165	6.069	-342382.598566
M34	-56399.948	26365.007	-26.475	1493245.023248
M32	-56385.036	26351.689	-32.731	1845538.613316
M27	-56402.333	26332.276	7.249	-408860.511917
			倍面積	-2074.772401
			面積	1037.3862005
			地積	1037.38 ㎡

基点座標一覧表

点名	X座標	Y座標	備考
0803	-56420.333	26374.238	基準点
T 1	-56387.052	26346.472	トラバー（鋲）

所在地	市原市東国分寺台二丁目2番7		
図種	境界確認図		
測地系	任意座標	受託番号	R07-175
		立会日	令和7年5月19日
座標系	任意座標	測量日	令和7年4月4日
		作成日	令和7年5月19日
縮尺係数	0.999910	縮尺	1／250
作成者	市原市ちはら台東六丁目1番 土地家屋調査士渡部事務所 土地家屋調査士・測量士 渡部		

原子一覧表用紙

街区番号	239
東国分寺台二丁目 2 番	

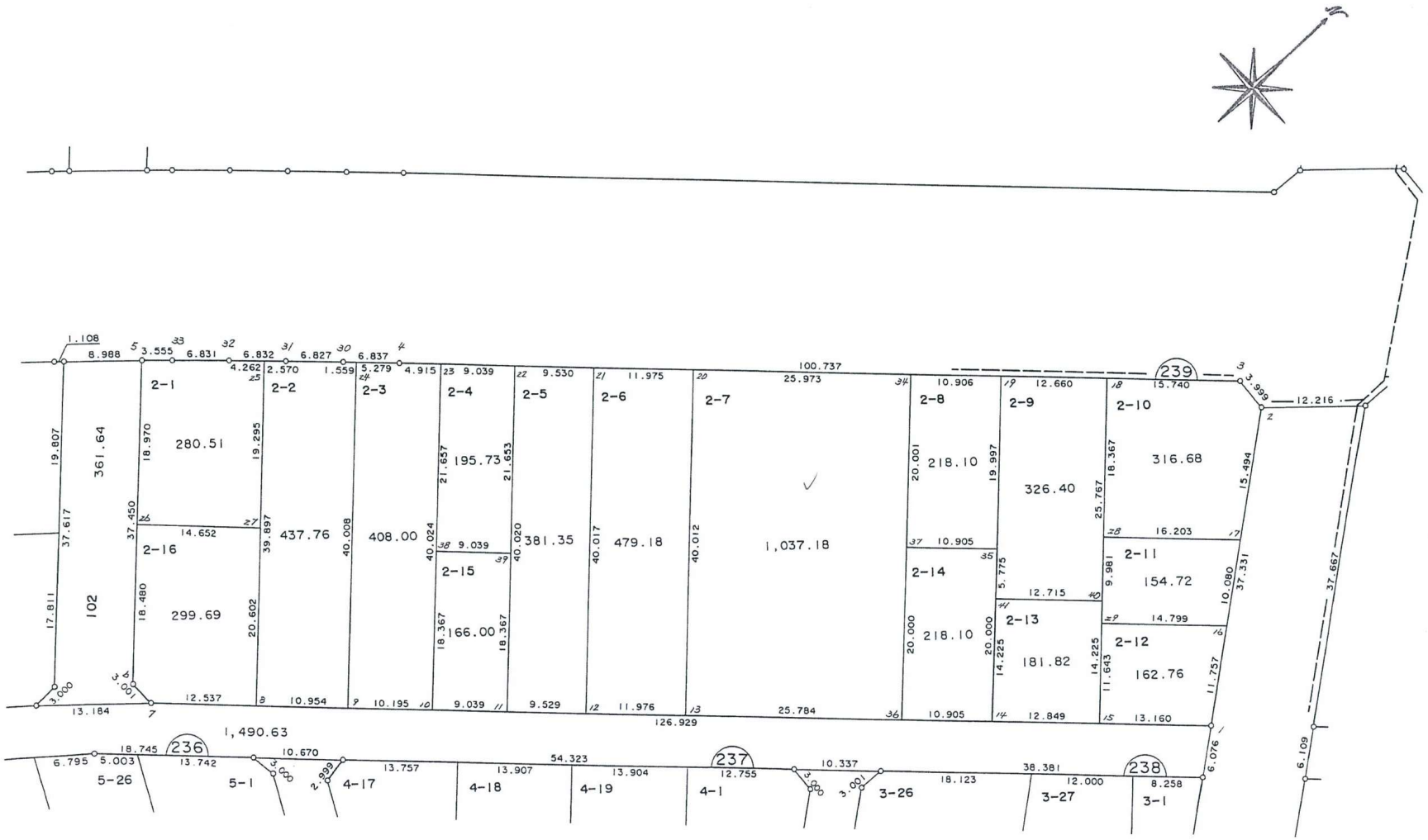

直角座標法面積計算書

市原市　東国分寺台二丁目　2番7

点名	X座標	Y座標	方向角	距離	ΔX	倍面積
239 BL 13	-56432.141	26358.930	318 14 27	40.012	-12.675	-334099.437750
239 BL 20	-56402.294	26332.282	48 16 0	25.973	-47.136	-1241198.444352
239 BL 34	-56385.005	26351.664	138 14 26	20.001	-2.369	-62427.092016
239 BL 37	-56399.925	26364.985	138 46 50	20.000	29.964	790000.410540
239 BL 36	-56414.969	26378.164	228 14 30	25.784	32.216	849798.931424
					合計 ...	2074.367846
					1／2 ...	1037.1839230
					面積 ...	1037.18 ㎡